Alain Muls alain.muls@gmail.com/Inbox

Subject:	FW: Verstoring GNSS-signalen Ruiselede 20/11/2025
From:	Jeffrey Verbeurgt <jeffrey.verbeurgt@ngi.be>
Date:	Tue, 9 Dec 2025, 10:33
Received:	Tue, 9 Dec 2025, 10:33
To:	Muls Alain <alain.muls@mil.be>, Alain Muls <alain.muls@gmail.com>, De Meulemeest [...]

Onderstaand een interessant voorval dat we bij FLEPOS hebben gehad.

NGI IGN

Jeffrey VERBEURGT | **G/Geodesie - Geodesist**
Nationaal Geografisch Instituut | Kortenberglaan 115 | 1000 Brussel
+32 (0)2 629 85 10 | **ngi.be**

From: Sébastien Roels <sebastien.roels@IBPT.be>
Sent: Tuesday, 9 December 2025 10:21
To: barbara.vandendriessche@vlaanderen.be
Cc: Jelle Verlooy <Jelle.Verlooy@BIPT.be>; Thierry Durand <thierry.durand@IBPT.be>; Serge Marotte <serge.marotte@IBPT.be>; NCS nl <NCS-nl@BIPT.be>; Depredomme Luc <luc.depredomme@vlaanderen.be>; Mussly Emile <emile.mussly@vlaanderen.be>; Jeffrey Verbeurgt <jeffrey.verbeurgt@ngi.be>; Thomas Gille <Thomas.Gille@BIPT.be>
Subject: RE: Verstoring GNSS-signalen Ruiselede 20/11/2025

You don't often get email from sebastien.roels@ibpt.be. Learn why this is important
CAUTION: This email originated from outside of the organization. Do not click links or open attachments unless you recognize the sender and know the content is safe.

Beste Barbara,

Bedankt voor uw bericht. Intern zijn wij niet op de hoogte van een jamming-oefening of het gebruik van GNSS-jammers op die data.
Op 20/11 vond er wel een jamming-oefening plaats in het Kamp van Lombardsijde (45 km in vogelvlucht van Ruiselede), maar deze duurde slechts enkele minuten en gebeurde met een laag

vermogen ("Civilian area out of effective jamming range (+1 km)").

Ik zal navragen bij mijn contactpersoon van Defensie of er iets gebeurd is op de RCS-site in Wingene.

Vraag: beschikt het FLEPOS-netwerk over een automatisch waarschuwingssysteem wanneer de C/N0 plots met enkele dB daalt voor alle satellieten? Bijvoorbeeld een plotse daling van 5 dB of meer op alle zichtbare satellieten. Ik denk dat het interessant zou zijn om zo'n functionaliteit te hebben, zodat we snel kunnen ingrijpen en de bron kunnen vinden. Bij het BIPT hebben we een permanentiedienst voor dit soort storingen op luchtvaartbanden, enz.

Ik houd u op de hoogte en kom bij u terug,

Sébastien Roels | Surveillance Department | Engineer-Advisor
Belgian Institute for Postal Services and Telecommunications
Allianz Tower | Boulevard du Roi Albert II 32 box 10 | 1000 Brussels
T +32 2 226 89 94 | **M** +32 474 39 79 91 | **www.bipt.be**

From: Vandendriessche Barbara <barbara.vandendriessche@vlaanderen.be>
Sent: Monday, December 8, 2025 3:30 PM
To: NCS nl <ncs-nl@bipt.be>
Cc: Depredomme Luc <luc.depredomme@vlaanderen.be>; Mussly Emile <emile.mussly@vlaanderen.be>; Jeffrey Verbeurgt <jeffrey.verbeurgt@ngi.be>
Subject: Verstoring GNSS-signalen Ruiselede 20/11/2025

U ontvangt niet vaak e-mail van barbara.vandendriessche@vlaanderen.be. Ontdek waarom dit belangrijk is

Beste,

Bij Digitaal Vlaanderen bieden wij met FLEPOS (Flemish Positioning Service) een kosteloze kwalitatieve Real Time Kinematic (RTK) dienstverlening waarbij correctiesignalen op basis van GNSS satellieten (waaronder GPS en Galileo) via mobiel internet worden verspreid. De correcties worden berekend op basis van een netwerk van vaste GNSS-referentiestations in Vlaanderen, plus enkele stations in omliggende regio's/landen. FLEPOS-gebruikers kunnen zo hun positie met cm-nauwkeurig bepalen. FLEPOS wordt gebruikt door landmeters, en voor machinesturing, precisielandbouw, drones, maritieme toepassingen etc.

Wij observeerden van 20/11/2025 omstreeks 6:30 UTC tot en met 21/11/2025 5:00 UTC drops in de signaalsterkte (C/N0) van de GNSS-signalen op ons FLEPOS GNSS-referentiestation in de Bruggesteenweg 130, 8755 Ruiselede.

Dit zien we op alle frequenties. Hieronder vinden jullie plots van GPS L1, L2 en L5 band:

-GPS L1:

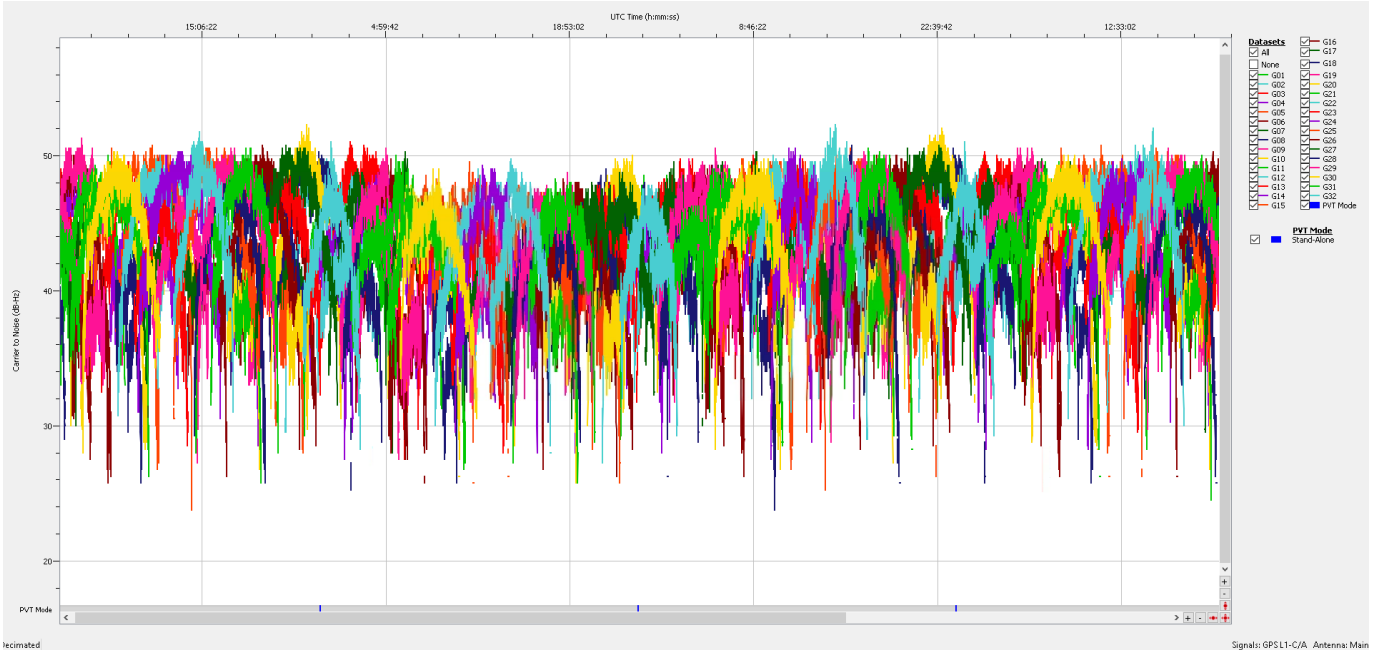

-GPS L2:

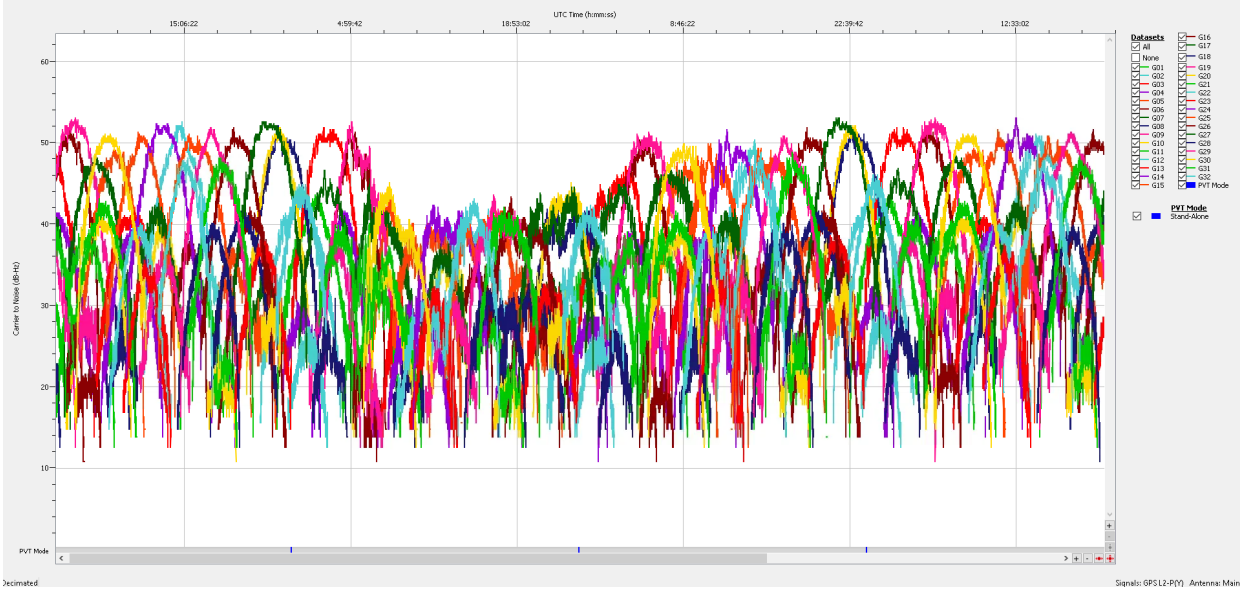

-GPS L5:

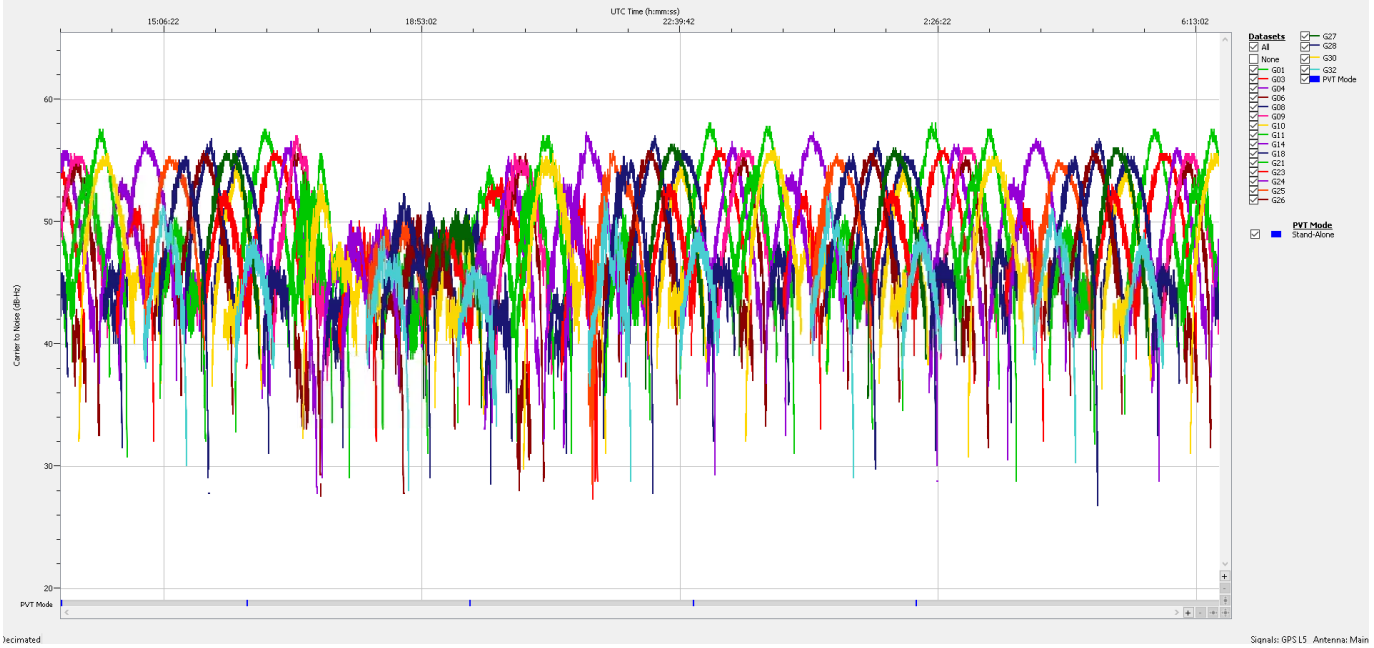

Tijdens deze periode registreerde onze software ook een sprong in de hoogte van onze antenne:

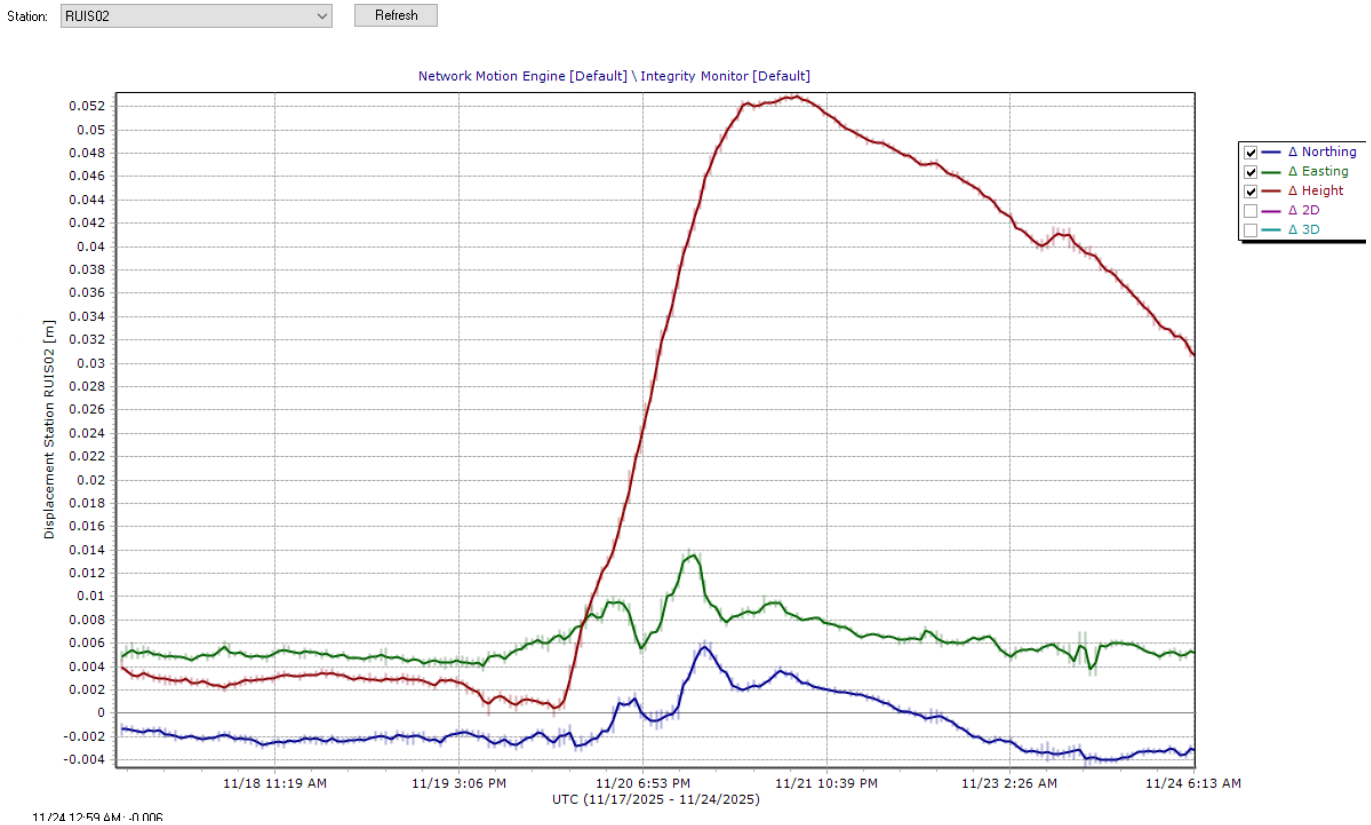

Het referentiestation bevindt zich dicht bij een site van Radio Communication Services (Defensie).
Is er bij het BIPT weet van wat de drops in de signaalsterkte zouden kunnen verklaren? Werden er tijdens die periode tests uitgevoerd, of signalen uitgestuurd die GNSS-signalen zouden kunnen verstoren?

Bij voorbaat dank,

Met vriendelijke groeten,

Barbara Vandendriessche

Product Owner FLEPOS

Team Basiskaart – Subteam FLEPOS

Afdeling Dataplatform

DIGITAAL VLAANDEREN

M +32 477 25 49 21

barbara.vandendriessche@vlaanderen.be

Ik werk niet op woensdag en vrijdag.

Havenlaan 88, 1000 Brussel | Koningin Maria Hendrikaplein 70, 9000 Gent

Wilt u post versturen? Gebruik dan ons postadres: Koning Albert II laan 15 bus 224, 1210 Brussel

Meer weten? Surf naar www.vlaanderen.be/digitaalvlaanderen

in

////////////